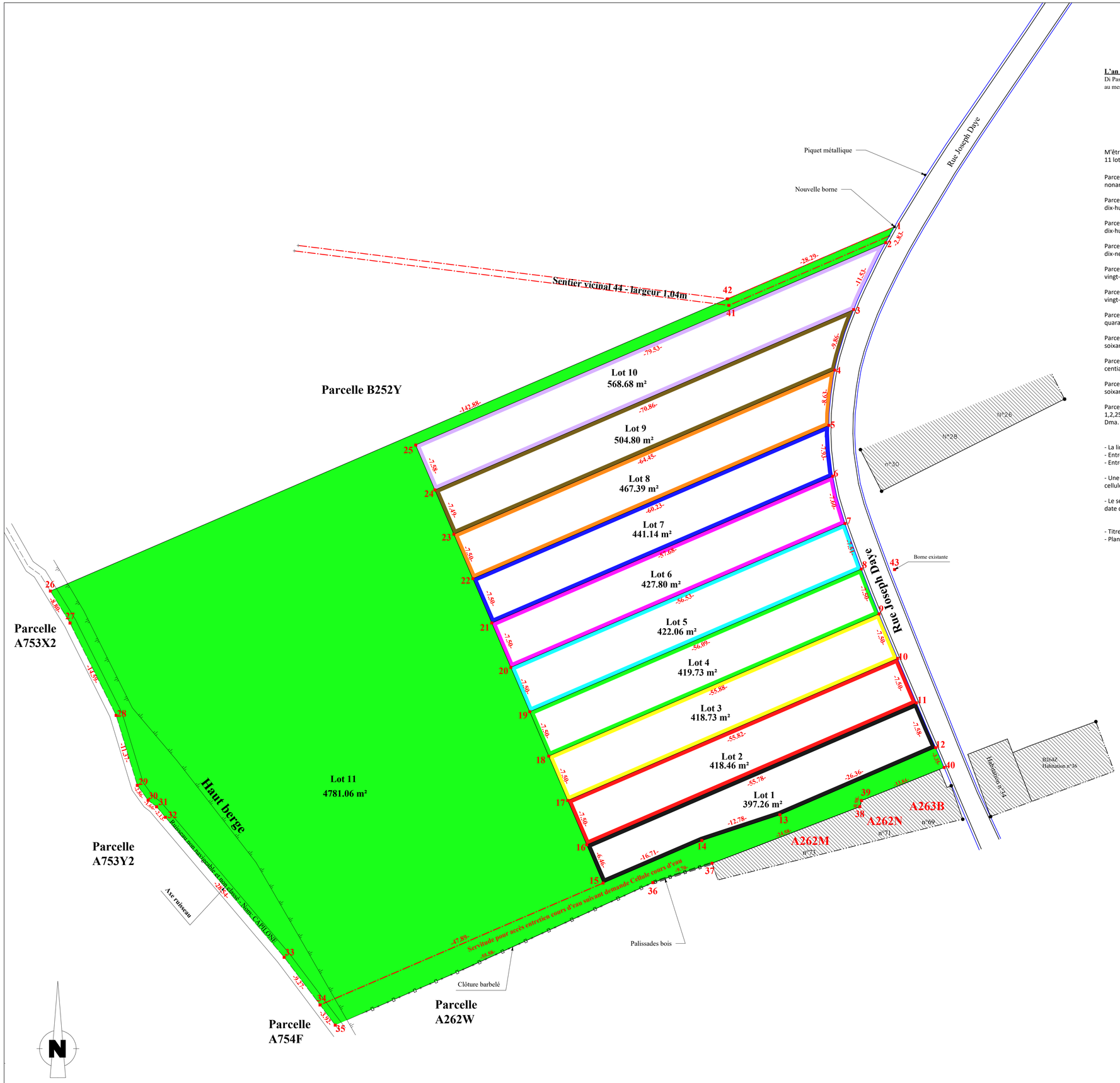

PROCES-VERBAL DE MESURAGE ET DIVISION:

PROCÈS-VERBAL DE MESURAGE ET DIVISION D'UN BIEN IMMEUBLE.

L'an deux mil vingt cinq, le 22 février,

Di Pasquale Gianni, Géomètre expert assermenté par le tribunal de 1er instance de Mons, inscrit au tableau des Géomètres-experts sous GEO 20/1523, déclare avoir procédé ce jour au mesurage du bien immeuble figuré au plan ci-contre et décrit ci-après afin de procéder au plan de mesurage, division et délimitation, à savoir :

Commune de FLEURUS
Rue Joseph Daye
Actuellement cadastrée ou l'ayant été sous:
FLEURUS 6 DIV/HEPPIGNIES/Section B 259F

Déclare :

M'être rendu ce jour sur la propriété cadastrée ou l'ayant été section B 259 F, en vue de procéder au mesurage de la parcelle afin de procéder à la division en 11 lots conformément au permis d'urbanisme obtenu et repris souf ref:URBA/20231025-112

Parcelle sous lisseré noir - lot 1: Une parcelle non bâti sous indices 11,12,13,14,15,16 avec une contenance après mesurage de 3 A 97 Ca 26 Dma. Trois ares nonante-sept centiares vingt-six décimiliares.

Parcelle sous lisseré rouge - lot 2: Une parcelle non bâti sous indices 10,11,16 et 17 avec une contenance après mesurage de 4 A 18 Ca 46 Dma. Quatre ares dix-huit centiares quarante-six décimiliares.

Parcelle sous lisseré jaune - lot 3: Une parcelle non bâti sous indices 9,10,17 et 18 avec une contenance après mesurage de 4 A 18 Ca 73 Dma. Quatre ares dix-huit centiares septante-trois décimiliares.

Parcelle sous lisseré vert - lot 4: Une parcelle non bâti sous indices 8,9,18 et 19 avec une contenance après mesurage de 4 A 19 Ca 73Dma. Quatre ares dix-neuf centiares septante-trois décimiliares.

Parcelle sous lisseré turquoise - lot 5: Une parcelle non bâti sous indices 7,8,19 et 20 avec une contenance après mesurage de 4 A 22 Ca 06 Dma. Quatre ares vingt-deux centiares six décimiliares.

Parcelle sous lisseréFuschia - lot 6: Une parcelle non bâti sous indices 6,7,20 et 21 avec une contenance après mesurage de 4 A 27 Ca 80 Dma. Quatre ares vingt-sept centiares quatre-vingt décimiliares.

Parcelle sous lisseré bleu - lot 7: Une parcelle non bâti sous indices 5,6,21 et 22 avec une contenance après mesurage de 4 A 41 Ca 14 Dma. Quatre ares quarante-et-un centiares quatorze décimiliares.

Parcelle sous lisseré orange - lot 8: Une parcelle non bâti sous indices 4,5,22 et 23 avec une contenance après mesurage de 5 A 67 Ca 39 Dma. Cinq ares soixante-sept centiares trente-neuf décimiliares.

Parcelle sous lisseré brun - lot 9: Une parcelle non bâti sous indices 3,4,23 et 24 avec une contenance après mesurage de 5 A 04 Ca 80 Dma. Cinq ares quatre centiares quatre-vingt décimiliares.

Parcelle sous lisseré mauve- lot 10: Une parcelle non bâti sous indices 2,3,24 et 25 avec une contenance après mesurage de 5 A 68 Ca 68 Dma. Cinq ares soixante-huit centiares soixante-huit décimiliares.

Parcelle sous teinte verte - lot 11: Une parcelle non bâti sous indices 1,2,25,24,23,22,21,20,19,18,17,16,15,14,13,12,40,39,38,37,36,35,34,33,32,31,30,29,28,27,26 et 25 avec une contenance après mesurage de 47 A 81 Ca 06 Dma. Quarante-sept ares quatre-vingt-un centiares six décimiliares.

Remarques :

- La limite passant parles points 26,27 et 28 est la limite reprise au plan cadastral.
- Entre les points 30,31,32 et 33, les façades arrières des constructions voisines sont à caractère privatives et propriété exclusive des voisins.
- Entre les points 28,29 et 30, les palissades en bois et les fils barbelés sont à caractère privatif et propriété exclusive des voisins.

- Une servitude reprise sous indice 12,13,14,15,3,35,36,37,38,39 et 40 d'une contenance après mesurage de 3A 63 CA 79 Dma, grève le lot 11 au profit de la cellule cours d'eau.

- Le sentier vicinal n°44 passant par les points 1,2,41 et 42 est le nouveau tracé proposé au comissaires voyer/Chef de division technique Xavier Appelmans en date du 29/11/2022.

Documents consultés :

- Titre de propriété associé à la parcelle cadastrée ou l'ayant été sous section B 259 F
- Plan mesurage et bornage du 26/06/2022 établi par mes soins

Liste de coordonnées Lambert 72:

N°	X	Y	Information
1	158891.064	128063.812	Nouvelle borne
2	158889.698	128061.336	Point limite non matérialisé
3	158884.716	128050.937	Point limite non matérialisé
4	158881.766	128041.528	Point limite non matérialisé
5	158880.855	128032.942	Point limite non matérialisé
6	158881.457	128025.036	Point limite non matérialisé
7	158883.354	128017.681	Point limite non matérialisé
8	158885.892	128010.614	Point limite non matérialisé
9	158888.650	128003.636	Point limite non matérialisé
10	158891.541	127996.715	Point limite non matérialisé
11	158894.459	127989.806	Point limite non matérialisé
12	158897.450	127982.842	Point limite non matérialisé
13	158873.246	127972.406	Point limite non matérialisé
14	158861.112	127968.403	Point limite non matérialisé
15	158845.768	127961.797	Point limite non matérialisé
16	158843.227	127967.740	Point limite non matérialisé
17	158840.278	127974.636	Point limite non matérialisé
18	158837.329	127981.532	Point limite non matérialisé
19	158834.380	127988.428	Point limite non matérialisé
20	158831.431	127995.322	Point limite non matérialisé
21	158828.482	128002.219	Point limite non matérialisé
22	158825.533	128009.115	Point limite non matérialisé
23	158822.582	128016.016	Point limite non matérialisé
24	158819.635	128022.907	Point limite non matérialisé
25	158816.655	128029.876	Point limite non matérialisé
26	158759.883	128007.184	Limite axe ruisseau
27	158762.937	128002.213	Limite axe ruisseau
28	158770.091	127987.864	Limite axe ruisseau
29	158773.387	127976.983	Limite axe ruisseau
30	158775.061	127974.663	Limite axe ruisseau
31	158776.383	127973.652	Limite axe ruisseau
32	158777.754	127972.018	Limite axe ruisseau
33	158796.213	127950.254	Limite axe ruisseau
34	158801.785	127942.851	Limite axe ruisseau
35	158804.144	127939.716	Limite axe ruisseau
36	158853.491	127961.864	Limite propriété
37	158862.716	127964.879	Coin bâtiment
38	158885.668	127973.673	Coin bâtiment
39	158885.925	127974.615	Coin bâtiment
40	158898.770	127979.766	Limite propriété
41	158865.316	128051.586	Limite sentier vicinal
42	158865.092	128052.601	Limite sentier vicinal

PLAN DE MESURAGE ET DIVISION:
Commune de FLEURUS
Rue Joseph Daye
Actuellement cadastrée ou l'ayant été sous:
FLEURUS 6 DIV/HEPPIGNIES/Section B 259F

Date	Echelle:	Format plan:	Numéro référence plan:	Unités de longueurs: m Unité de surfaces: m²
22-02-2025	1/300	A1		

PROCÈS-VERBAL DE MESURAGE ET DIVISION D'UN BIEN IMMEUBLE.

L'an deux mil vingt cinq, le 22 février,

Di Pasquale Gianni, Géomètre expert assermenté par le tribunal de 1er instance de Mons, inscrit au tableau des Géomètres-experts sous GEO 20/1523, déclare avoir procédé ce jour au mesurage du bien immeuble figuré au plan ci-contre et décrit ci-après afin de procéder à la division, à savoir :

Commune de FLEURUS
Rue Joseph Daye
Actuellement cadastrée ou l'ayant été sous:
FLEURUS 6 DIV/HEPPIGNIES/Section B 259F

Remarques :

- La limite passant parles points 26,27 et 28 est la limite reprise à l'axe du cours d'eau de type non navigeable et non classé. Nom: CAPILONE
- Entre les points 30,31,32 et 33, les façades arrières des constructions voisines sont à caractère privatives et propriété exclusive des voisins.
- Entre les points 28,29 et 30, les palissades en bois et les fils barbelés sont à caractère privatif et propriété exclusive des voisins.

- Une servitude reprise sous indice 12,13,14,15, 27,28,29,30,31,32 et 33, d'une contenance après mesurage de 3A 58 CA 84 Dma, grève le lot 11 au profit de la cellule cours d'eau.

- Le sentier vicinal n°44 passant par les points 1,2,36 et 35 est le nouveau tracé proposé au comissaires voyer/Chef de division technique Xavier Appelmans en date du 29/11/2022.

Documents consultés :

- Titre de propriété associé à la parcelle cadastrée ou l'ayant été sous section B 259 F
- Plan mesurage et bornage du 26/06/2022 établi par mes soins

Signature:



Géomètre Landmeter

Di Pasquale Gianni
Géomètre-Expert assermenté
GEO 20/1523
Rue du Grand pont 62
7012 Jemappes
0478228477
info@capital-immo.expert

Légende:

- Station
- BE Borne existante
- BN Borne nouvelle
- BC Borne communale
- Point mesuré
- Taque egout
- Talus
- Arbre
- Habitation
- Poteau électrique
- Avaloir
- Clôture treillis

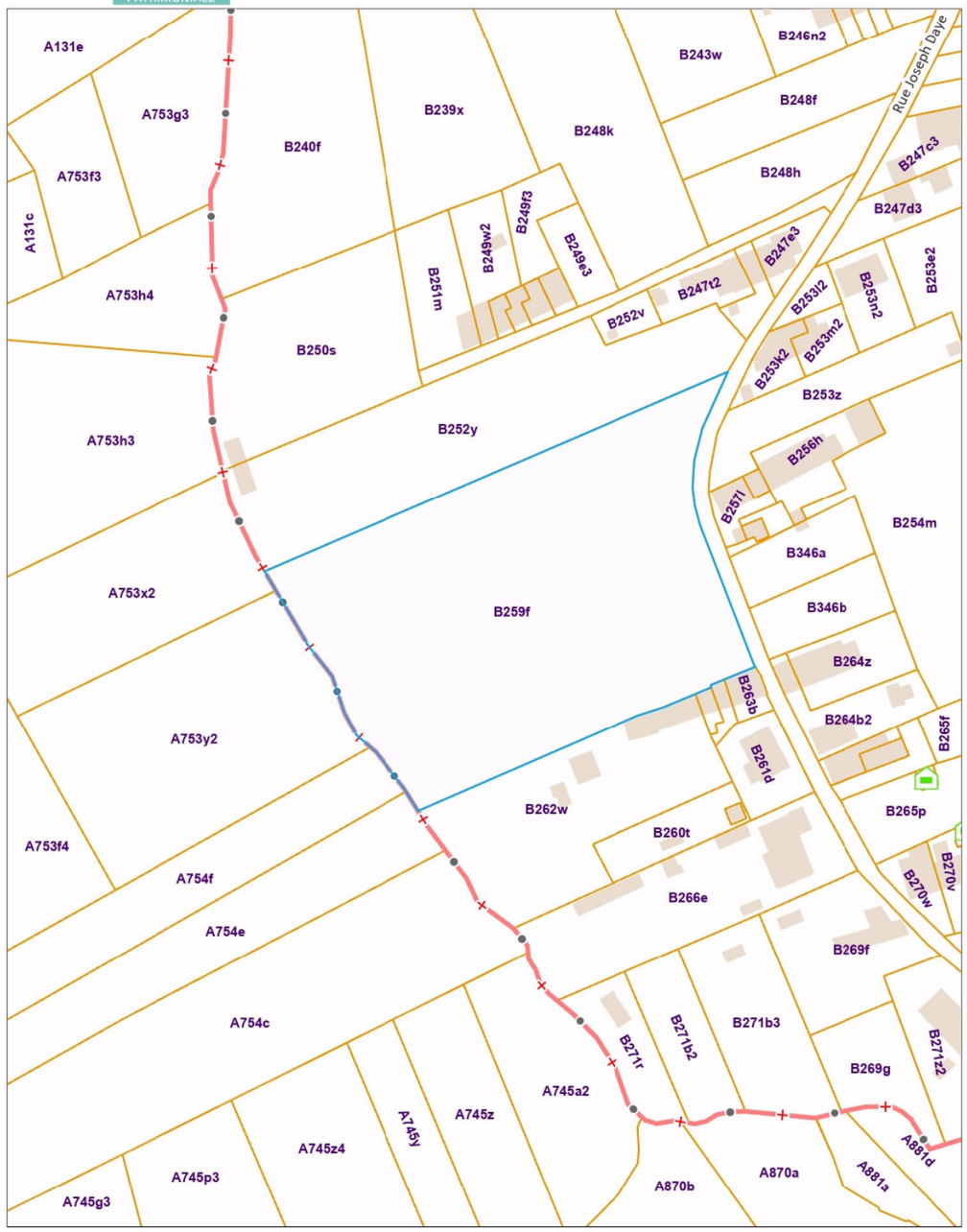

L'AGDP est l'auteur du plan parcellaire cadastral et le producteur de la base de données de laquelle les données sont reprises et jouit de la propriété intellectuelle comme repris dans la loi sur les droits d'auteurs et les droits des bases de données. Depuis le 01/01/2018 les bâtiments du plan parcellaire cadastral seront repris progressivement et remplacés par un set de données (= Bpn_ReBu autrement dit Bâtiment Régionaux) géré par les régions. L'AGDP ne sera dès lors plus responsable pour la représentation des bâtiments sur le plan parcellaire cadastral.